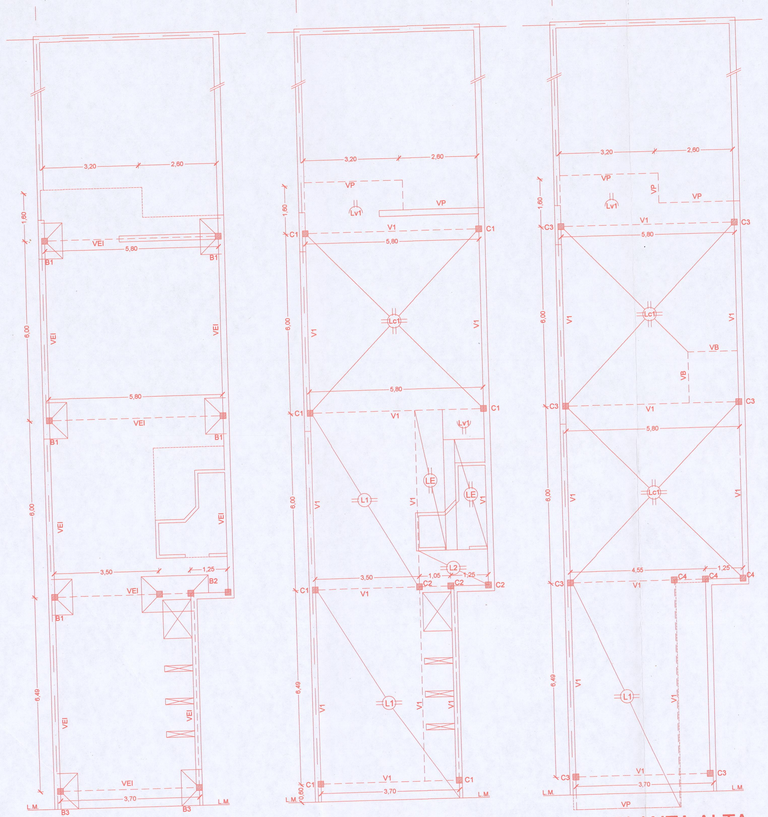


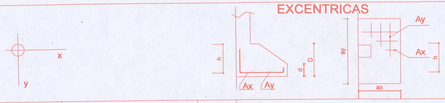
PLANTA FUNDACIONES

PLANTA BAJA
NIVEL +3,70

PLANTA ALTA
NIVEL +6,50

PLANILLA DE PILARES

EXCENTRICAS



Hormigon - H17
Acero Tipo III - 4200 Kg/cm2

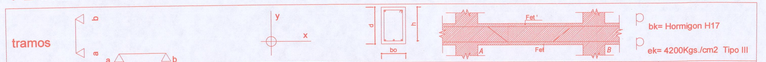
Nivel	design.	N	S	DIMENSIONES m					M	Armaduras Ax			Armaduras Ay			observaciones
		Tn/m	m2	ax	ay	d	D	h	(Tm)	cm2	Ø	Sep	cm2	Ø	Sep.	
PB	B2	1,50	1,50	1,50	1,00	0,15	0,20	0,70	1,32	4,2	10	12	3,7	10	15	
	B3	1,75	3,25	2,50	1,50	0,15	0,20	0,70	2,10	5,65	10	10	5,65	10	10	DOBLES
	VF						0,20	0,20			10			10		2 Ø POR ARRIBA 2Ø POR ABAJO ESTRIBOS Ø6 c/0,25 m.

PLANILLA DE LOSAS

UBICACION	POSICION	Luz Y / X m	q kg/m²	M tm	h_y / h_x cm	D	ARMADURAS Fe sec cm²/m	Ø m m	SEP	Fe sec cm²/m	Ø m m	SEP	REPARTICION Ø	REPARTICION SEP	OBSERVACIONES
P.B. - P.A.	Lc1	6,00	0,70	2,10	10	12,0	4,28	10	12	-	-	-	-	-	Adicionar sobre apoyo Ø12 cada 24cm.
		6,00	0,70	2,10	10	12,0	4,28	10	12	-	-	-	-	-	
	L1	3,70	0,70	0,96	10	12,0	3,25	10	15	-	-	-	6	20	
	L2	2,50	0,70	0,55	10	12,0	2,60	10	20	-	-	-	6	20	
	LV	1,50	0,70	0,79	10	12,0	-	-	-	3,12	10	20	6	20	
	LE	4,50	0,70	1,42	12	14,0	5,20	12	12	-	-	-	6	20	

PLANILLA DE VIGAS

tramos



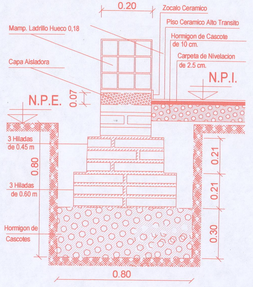
hormigon H17
acero Tipo III=4200 Kg/cm2

nivel	design.	luz (m)	forma	p tn	q t/m	reacc tn Ra	reacc tn Rb	M (+) tm	dimensiones cm b	do	h	armadura - tramo Fet cm2	Ø	nº	Fet' cm2	nº	Ø	nº	hierro a doblar y/o adicional A Ø	nº	B Ø	nº	tension de corte kg/cm2 A	B	estrib. cerr. Ø	sep cm	observaciones
PB-PA	V 1	5,80		--	2,48	7,24	7,24	3,56	20	42	45	4,8	16 12	2 2	-	-	-	2	16	2	16	11.8	11.2	6	10/20	CONTINUA	
	V P								15	42	45		12	4		2	10					-	-	6	15		
	V B								20	42	45		12	3		2	10							6	15		

PLANILLA DE COLUMNAS

POSIC.	FORMA	hp p	P t	Fb d1	Fb d2	Fb cm2	Fe cant	Fe Ø	Fe cm2	ESTRIBOS Ø	ESTRIBOS Sep.	W	Wpo Kg/m2	OBSERVACIONES
													Hormigon H17 Acero Tipo III=4200 Kg/m2	
C1		4,00	11,00	25	20	500	4	12	3,73	6	12	1,02	170	
C2		4,00	4,50	20	20	400	4	12	2,56	6	15	1,02	170	
C3		3,00	6,20	25	20	500	4	12	3,73	6	12	1,02	170	
C4		3,00	2,25	20	20	400	4	12	3,73	6	15	1,02	170	

DETALLE DE CIMIENTOS PARA MUROS DE 0.20



DESTINO DE LA OBRA : VIVIENDA UNIFAMILIAR

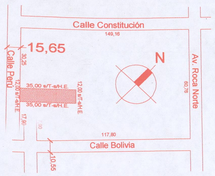
PROPIETARIO : SUCESIÓN DE JULIO RICARDO DIAZ
AMANDA ARGENTINA ORTÍZ GIMEZ
L.E. : 5.960.320 CUIL : 27-5960320-5

UBICACIÓN : PERÚ N° 1025
BARRIO : DR. JUAN BAUTISTA ALBERDI
CIUDAD : CAPITAL - SANTIAGO DEL ESTERO
ESCALA : 1 : 100 - 1 : 200

RELEVAMIENTO Y AMPLIACION

SUPERFICIE DE TERRENO :	420,00 m2 S/T - S/H.e.
SUP. CUB. EXIST. :	111,39 m2
SUP. CUBIERTA AMPL. P.B.	102,42 m2
SUP. CUBIERTA AMPL. P.A.	105,95 m2
SUP. CUB. FUERA LM	0 m2
SUP. CUBIERTA TOTAL :	319,76 m2

CROQUIS DE UBICACION



PROPIETARIO :
DOMICILIO : Amanda Ortiz Gimez
Julio Diaz

RELEVAMIENTO :
DOMICILIO :
HUGO V. CAROL
ARQUITECTO - Mat. Nº 0033

PROYECTO :
DOMICILIO :
HUGO V. CAROL
ARQUITECTO - Mat. Nº 0033

DIRECCIÓN DE OBRA :
DOMICILIO :

CATEGORIA COLEGIO DE ARQUITECTOS: "B"

ANCHO DE CALLE :	15,65 m
ANCHO DE VEREDA :	3,85 m
ANCHO DE CALZADA :	8,00 m
PAVIMENTO :	SI
SERVICIOS CLOACALES :	SI

DESIGNACION : PLANO DE ESTRUCTURAS 2

OBSERVACIONES :

Las referencias al Título de Dominio son meramente indicativas, y la aprobación administrativa no valora los derechos que de ellos emergen

24 OCT 2018

PERMISO DE COMIENZO DE OBRA Nº 4402
DIRECCION DE SUELO URBANO

MUNICIPALIDAD DE LA CIUDAD DE SANTIAGO DEL ESTERO
SECRETARIA DE PLANEAMIENTO Y OBRAS PUBLICAS
APROBADO
DIRECCION DE SUELO URBANO
EXPEDIENTE 17-S-2018
FECHA 31 DIC 2018

DIRECCIÓN DE SUELO URBANO
EXPEDIENTE 17-S-2018
FECHA 24/10/18
BOLETA 58875

SRO. AGUSTIN MARIO J. LOPEZ
Dpto. CATASTRO
Dirección de Suelo Urbano

Arq. RAUL E. MARTINEZ
SERVICIO DE OBRAS PRIVADAS
DIRECCION DE SUELO URBANO

Arq. BERNARDO L. M. SANTILLAN
DIRECTOR
DIRECCION DE SUELO URBANO
MUNICIPALIDAD DE SGO. DEL ESTERO