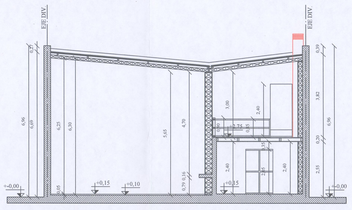
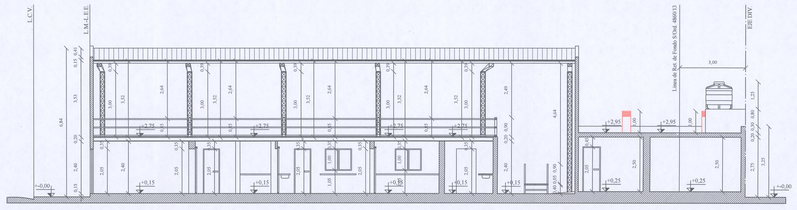


FACHADA S/ CALLE ANTONINO TABOADA



CORTE B-B



CORTE A-A

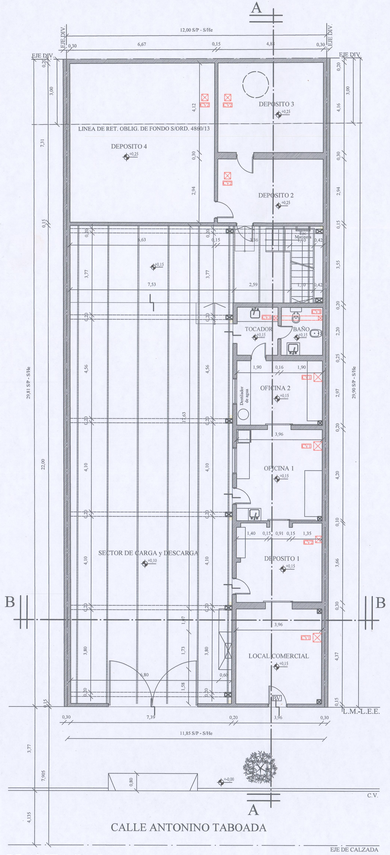
PLANILLA DE ILUMINACION Y VENTILACION

LOCAL		ABERTURAS					OBSERVACIONES
DESIGNACION	SUPERFICIE	DESIG.	ANCHO	ALTO	AREAS I.	AREAS V.	
PLANTA BAJA							
LOCAL COMERCIAL	17,22	PV	0,90	2,05	1,84	1,84	Dos Puertas Ventanas
DEPOSITO 1	14,17	CV1	0,40	0,40		0,16	Conducto de Ventilacion a Colocar
OFICINA 1	16,59	CV2	0,30	0,30		0,09	Conducto de Ventilacion a Colocar
OFICINA 2	11,72	CV1	0,40	0,40		0,16	Conducto de Ventilacion a Colocar
TOCADOR	4,18	CV3	0,20	0,20		0,04	Conducto de Ventilacion a Colocar
BAÑO	4,18	CV3	0,20	0,20		0,04	Conducto de Ventilacion a Colocar
SECT. CARGA y DESC.	169,68	PM	4,10	3,20		13,12	Porton Metalico
		Vo	4,10	1,54	6,31	6,31	Vano
DEPOSITO 2	14,35	CV2	0,30	0,30		0,09	Conducto de Ventilacion a Colocar
DEPOSITO 3	20,19	CV2	0,30	0,30		0,09	Conducto de Ventilacion a Colocar
DEPOSITO 4	48,78	CV2	0,30	0,30		0,09	Conducto de Ventilacion a Colocar
PLANTA DE ENTREPISO							
DEPOSITO 5	73,29	Vo	4,10	1,54	6,31	6,31	Vano
		CV1	0,40	0,40		0,48	Tres Conductos de Vent. a Colocar
		CV2	0,30	0,30		0,09	Conducto de Ventilacion a Colocar
		CV3	0,20	0,20		0,04	Conducto de Ventilacion a Colocar

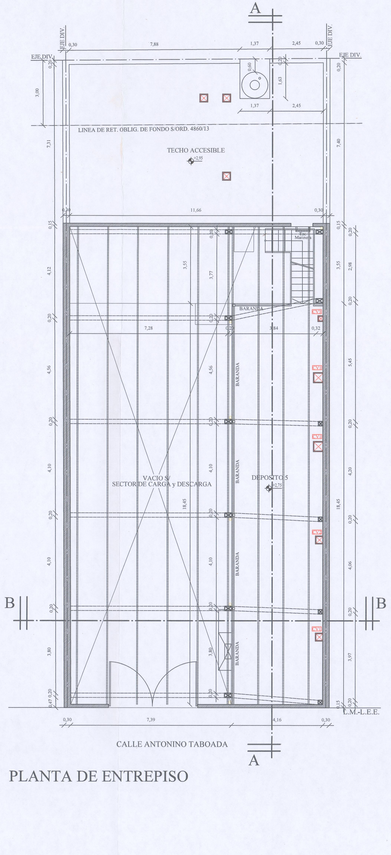
PLANIMETRIA
ESCALA 1:200



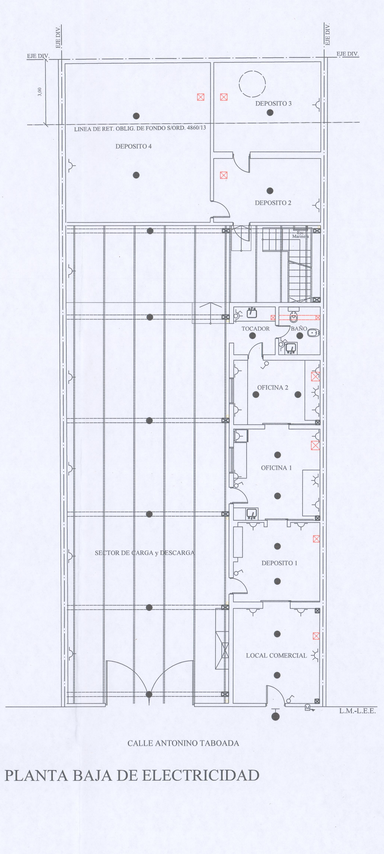
REFERENCIAS ELÉCTRICAS	
	MEDIDOR Y TOMA A TIERRA
	TABLERO PRINCIPAL
	TABLERO SECCIONAL
	BOCA DE UNO Y DOS EFECTOS
	BOCA DE PARED
	TOMA CORRIENTE
	CAJA DE DISTRIBUCION
	LLAVES, UNO,DOS y TRES PUNTOS
	LINEA GENERAL
	CIRCUITO DE AIRE ACONDICIONADO
	CAÑO DE SUBIDA Y ENTRADA DE ENERGIA
	LLAVE DE COMBINACION SIMPLE



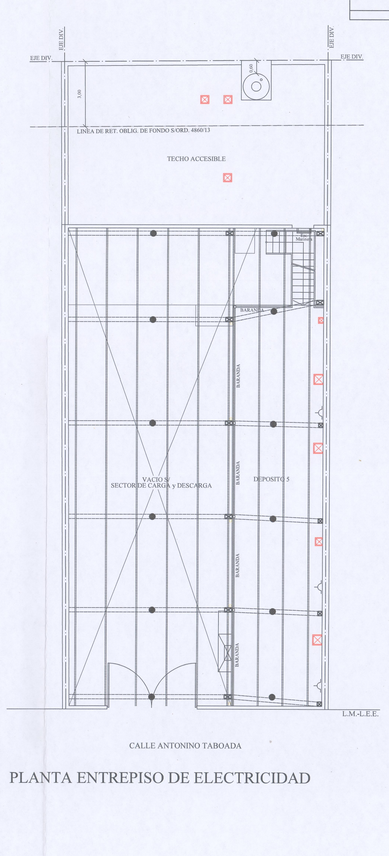
PLANTA BAJA



PLANTA DE ENTREPISO



PLANTA BAJA DE ELECTRICIDAD



PLANTA ENTREPISO DE ELECTRICIDAD



PLANTA DE TECHOS

DIST. : 03 ZONA : 03 MANZ. : 02 PARC. : 100
PADRON INMOB. : 01-01-111798 I.C.M. : 220-B-2024 DOMINIO : 7N-7995/A
01-01-111799 7N-7995/B

LEY 4683
VISADO ELECTRONICO
C.U.I.T. 30-71108810

DEST. DE LA OBRA : OFICINA - DEPOSITO

PROPIETARIO : BERNARDO BAUTISTA BAILON (U.F. "A" y "B")
D.N.I. N° 34.693.069 - C.U.I.L/T.: 20-34693069-2

UBICACION : CALLE ANTONINO TABOADA N° 448 / 452

BARRIO : Dr. JUAN BAUTISTA ALBERDI

CIUDAD : CAPITAL - SANTIAGO DEL ESTERO

ESCALA : 1 : 100 - 1 : 250

DIRECCION DE SUELO URBANO 818-31-24 Expediente N° DIC. 2024 Planos N° 3434

SUP. DE TERRENO : 356,01 m2 S/P-S/He
SUP. CUBIERTA PLANTA BAJA : 356,01 m2
SUP. CUBIERTA ENTREPISO : 80,16 m2
SUP. CUBIERTA TOTAL : 436,17 m2

CROQUIS DE UBICACION



ANCHO DE CALLE : 16,12 m
ANCHO DE VEREDA : 3,77 m
ANCHO DE CALZADA : 8,27 m

PROPIETARIO :
DOMICILIO :

RELEVAMIENTO :
DOMICILIO :
AGUSTIN BAILON INGENIERO C. P. N° M.P.N° 3579

ELECTRICIDAD :
DOMICILIO :

CATEG. DEL CONSEJO DE INGENIEROS : "A"

PAVIMENTO : Calidad de la Calle
SERVICIOS : EQUIPAMIENTOS

DESIGNACION : PLANO DE RELEVAMIENTO

OBSERVACIONES :
Las referencias al título de dominio son meramente indicativas, y la aprobación administrativa no valora los derechos que de ellos emergen.

MUNICIPALIDAD DE LA CIUDAD DE SANTIAGO DEL ESTERO
SECRETARIA DE ECONOMIA
APROBADO
DIRECCIÓN DE SUELO URBANO
EXPEDIENTE: 818-31-2024 Cpo. 12 - Fs. 24
FECHA: 28 MAR 2025

EL QUE YO DESTINO DE LOS LOCALES DE REFERENCIA SE AJUSTA A LAS DISPOSICIONES DE LA ORDENANZA N° 7883/2 CAPITULO 2.

ARQ. ABRAHAM BERNARDO ROMERA
Dpto. OBRAS PRIVADAS
DIRECCION DE SUELO URBANO

ARQ. ESTER R. CHALUB
SUB-DIRECTORA
DIRECCION DE SUELO URBANO