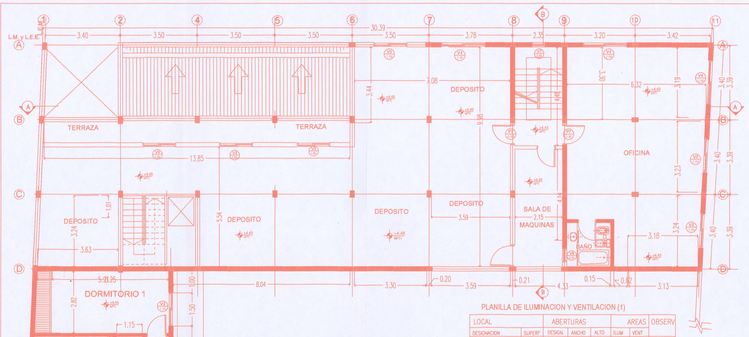
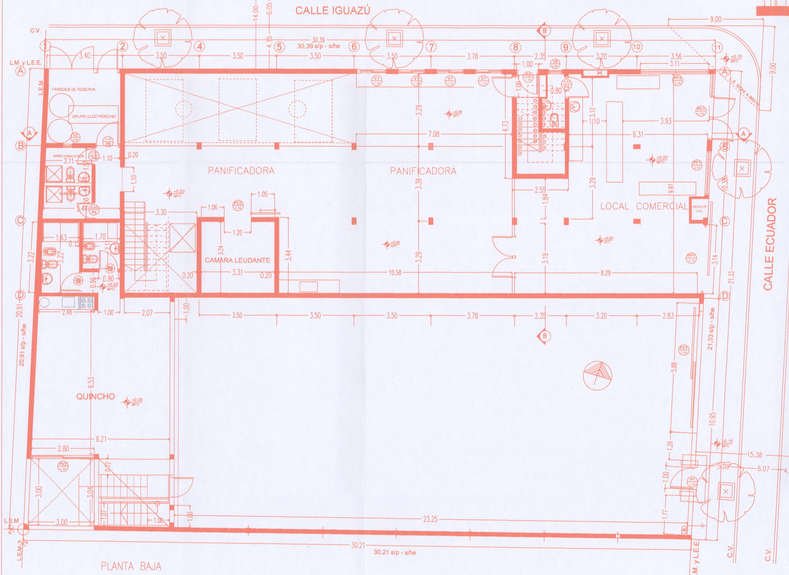


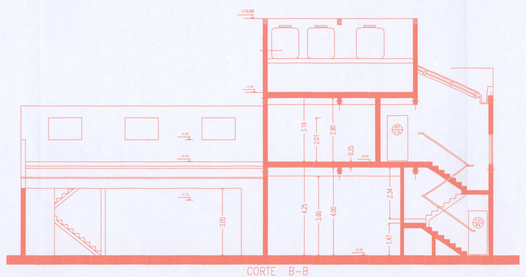
PLANTA 1° PISO NIVEL +4.45


PLANILLA DE ILUMINACION Y VENTILACION (1)


LOCAL		ABERTURAS				AREAS	OBSERV.
DESIGNACION	SUPERF.	DESIGN.	ANCHO	ALTO	ILUM.	VENT.	
INGRESO – ESCALERA	26.09	V1 (2)	0.80	1.00	0.80	0.80	
LOCAL COMERCIAL	77.44	PV 1	2.00	2.00	8.40	4.40	
		PF1	2.00	3.00	8.40	----	
		PF2	3.00	3.00	9.00	----	
BAÑO EN LOCAL		V5	0.60	0.40	0.24	0.12	
PANIFICACION	186.78	V1 (4)	1.20	1.00	4.80	4.80	
BAÑO CABALLEROS	3.30	V2	0.40	0.25	0.10/4	0.10/4	
BAÑO DAMAS	3.25		VENTILA	POR	CONDUCTO		
OFICINA PLANTA ALTA	57.22	V4 (2)	2.00	1.00	2.00	1.00	
	24.85	V3 (2)	1.50	1.00	1.50	0.75	
BAÑO 1	3.00	V5	0.60	0.40	0.24	0.12	
ESCALERA	9.63	V7	0.80	1.00	0.80	0.80	
DEPOSITO	148.00	V4	2.00	1.00	2.00	1.00	
		V3 (4)	1.50	1.00	1.50	0.75	
QUINCHO PLANTA BAJA	53.80	PV2	2.00	2.00	5.60	2.80	
BAÑO DAMAS	5.28		VENTILA	POR	CONDUCTO		
BAÑO CABALLEROS	3.58		VENTILA	POR	CONDUCTO		
DESIGNACION	SUPERF.	DESIGN.	ANCHO	ALTO	ILUM.	VENT.	
QUINCHO 1° PISO	47.43	V7 (2)	0.80	1.00	0.80	0.80	
DORMITORIO 1	16.84	V3	1.50	1.00	1.50	0.75	
DORMITORIO 2	14.32	V3	1.50	1.00	1.50	0.75	
BAÑO QUINCHO 1°PISO	6.06		VENTILA	POR	CONDUCTO		

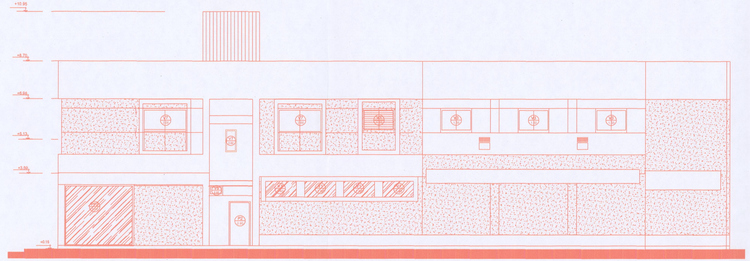


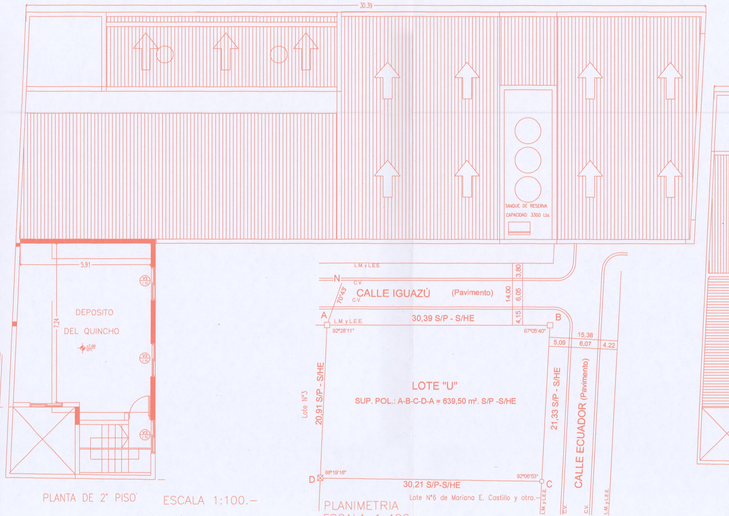
PLANTA BAJA











PLANTA DE 2° PISO ESCALA 1:100.–

PLANIMETRIA ESCALA 1:400.–



PLANTA DE TECHOS

SUPERFICIE TERRENO		639,50 m²
FOS%	60%	383,70 m²
FOT	1,5	959,25 m²

PLANILLA DE SUPERFICIES

PISO	SUPERFICIE
PLANTA BAJA	364,64 m²
PLANTAS 1° PISO	320,45 m²
PLANTAS 2° PISO	61,05 m2
TOTAL	746,14 m2

DIST. : 02 ZONA : 10 MANZ. : 15 (D2) PARC.:015/016–020 LEY 4683

PADRON INMOB.: 01–1–148890 (C.M.:N°161–F–2024 DOMINIO : 7S–38–291
01–1–148891 7S–38–292

24080769

DEST. DE LA OBRA : LOCAL COMERCIAL PANADERIA _ DEPOSITO_ DEPARTAMENTOS

PROPIETARIO: **GRACIELA ELIZABETH FERNANDEZ**

DNI : 22.243.740 CUIL : 27–22243740–

UBICACION : CALLE ECUADOR ESQUINA IGUAZU S/N

BARRIO : AMERICA DEL SUR

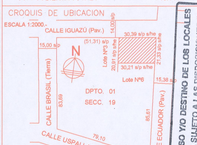
CIUDAD : CAPITAL – SANTIAGO

ESCALA : 1:100 – 1:200

SUP. DE TERRENO : s/p - s/he 639.50 m²
SUP. CUBIERTA : 746.14 m²
SUP. FUERA DE L. MUNICIPAL: 00.00 m²
SUP. CUBIERTA TOTAL: 746.14 m²

PROPIETARIO : GRACIELA ELIZABETH FERNANDEZ

CROQUIS DE UBICACION
ESCALA 1:2000



CONSEJO : PUEYRREDON N°206 - B° AUTONOMA

PROYECTO : ALEJANDRO RODRIGUEZ PAZ ARQUITECTO

CONSEJO : JOSE OLASCHEA N°206 - B° AUTONOMA

DIRECCION TECNICA : ALEJANDRO RODRIGUEZ PAZ ARQUITECTO

CONSEJO : JOSE OLASCHEA N°206 - B° AUTONOMA

CATEGORIA COLINDANTE : RESIDENCIAL

	ECUADOR	IGUAZU	
ANCHO DE CALLE :	15,38 m	14,00 m	PAVIMENTO :
ANCHO DE VEREDA :	5,09 m	4,15 m	SERVICIOS CLOACALES :
ANCHO DE CALZADA :	6,07 m	6,05 m	

DESIGNACION :

PLANO GENERAL

OBSERVACIONES :

Las referencias al Título de Dominio son meramente indicativas, y la aprobación administrativa no valora los derechos que de ellos emergen.

EL SUSCRITO PROFESIONAL MATRICULADO DECLARA BAJO JURAMENTO QUE LOS DATOS CONSIGNADOS EN EL PRESENTE PLANO SON EXACTOS Y SE ADECUAN A LA REALIDAD, ASUMIENDO LA RESPONSABILIDAD QUE ESTABLECE LA LEY 4683 Y SU DECRETO REGLAMENTARIO.

PERMISO DE COMIENZO DE OBRA N° 2024/1/1/1
DIRECCION DE SUELO URBANO

Ing. Agrim. C. LEANDRO ARJONA
JEFE DE AREA DE VISACIONES TECNICAS
DIRECCION DE CATASTRO MUNICIPAL

MUNICIPALIDAD DE LA CIUDAD DE SANTIAGO DEL ESTERO
SECRETARIA DE ECONOMIA
APROBADO
DIRECCION DE SUELO URBANO
EXPEDIENTE: 777-31-2024 – Cpd: CBE-2024
FECHA: 18 ABR 2025

Arq. ABRAHAM BERNARDO ROMINA
Fisc. OBRAS PRIVADAS
DIRECCION DE SUELO URBANO

Arq. Cesar Marcelo Abt
Director D.S.U.
Municipalidad de la C.

Alejandro Rodriguez Paz
ARQUITECTO
Mat. Prof. N°826

EL INSCRIPTO DECLARA BAJO JURAMENTO QUE LOS DATOS CONSIGNADOS EN EL PRESENTE PLANO SON EXACTOS Y SE ADECUAN A LA REALIDAD, ASUMIENDO LA RESPONSABILIDAD QUE ESTABLECE LA LEY 4683 Y SU DECRETO REGLAMENTARIO.

PROYECTO Y DIRECCION DE OBRA
SUSANA ABECASSIS
Arquitecta
Secretaria Técnica
Colegio de Arquitectos SDE

04 ENE 2025

DIRECCION DE SUELO URBANO
EXPEDIENTE: 777-31-2024
FECHA DE ENTRADA: 03 ACT 2025
FOLIO: 336

SECRETARIA DE ECONOMIA
Municipalidad de la Capital
DPTO. DE SUELO URBANO

DIRECCION DE SUELO URBANO
EXPEDIENTE: 777-31-2024
FECHA DE ENTRADA: 27 DIC 2024
FOLIO: 3370